Geografia da População: Distribuição Espacial, Migrações e Dinâmicas Demográficas

You.com ARI

JUNE 2025

Contents

Introdução 2
2.1 Distribuição Espacial da População no Brasil e no Mundo 2
Fatores Históricos, Naturais, Econômicos e Políticos 2
Distribuição Espacial da População no Brasil 2
Padrões Globais de Concentração e Vazios Demográficos 3
2.2 Grandes Movimentos Migratórios Internacionais e Intranacionais 3
Conceitos Fundamentais e Tipologias Migratórias 3
Fluxos Migratórios Internacionais Contemporâneos: Sul-Norte e Sul-Sul 5
Migrações Internas no Brasil 6
Migração, Refúgio e Deslocamento Forçado 6
Migração e Mudanças Climáticas 7
2.3 Dinâmica Populacional e Indicadores da Qualidade de Vida das Populações 7
Principais Conceitos e Indicadores Demográficos 8
Indicadores de Qualidade de Vida 9
Conclusão 10
Questões para Autoavaliação (Active Recall) 11
References 14

Introdução

A Geografia da População é um campo essencial para a compreensão das dinâmicas territoriais, sociais e econômicas que moldam o Brasil e o mundo contemporâneo. A análise da distribuição espacial da população, dos movimentos migratórios e da dinâmica demográfica revela padrões complexos, historicamente construídos e em constante transformação, que refletem e influenciam as condições de vida, o desenvolvimento regional e as desigualdades socioespaciais. No contexto do Concurso de Admissão à Carreira de Diplomata (CACD), dominar esses conceitos é fundamental para interpretar criticamente os desafios e oportunidades do Brasil no cenário internacional e interno, articulando causas, consequências e inter-relações entre os fenômenos populacionais.

2.1 Distribuição Espacial da População no Brasil e no Mundo

A distribuição da população mundial é notoriamente desigual, resultado de uma interação multifacetada entre fatores históricos, naturais, econômicos e políticos. O conceito de áreas ecúmenas refere-se às regiões permanentemente habitadas, enquanto as áreas anecúmenas correspondem aos chamados vazios demográficos, onde a ocupação humana é rarefeita ou inexistente devido a condições ambientais adversas ou limitações históricas. [1]

> [!definition] **Áreas Ecúmenas e Anecúmenas** > - **Ecúmenas:** Regiões permanentemente habitadas, com densidade populacional significativa e infraestrutura consolidada. > - **Anecúmenas:** Vazios demográficos, áreas com ocupação humana rarefeita ou inexistente devido a fatores naturais (clima extremo, relevo acidentado, solos inférteis, isolamento geográfico) ou históricos. [2]

Fatores Históricos, Naturais, Econômicos e Políticos Historicamente, a ocupação humana concentrou-se em regiões de clima ameno, solos férteis, disponibilidade de água e acesso a rotas comerciais. Grandes civilizações floresceram em vales fluviais (Nilo, Ganges, Yangtzé), planícies costeiras e regiões de clima temperado. Em contrapartida, desertos (Saara, Atacama), áreas polares (Groenlândia, Sibéria), florestas densas (Amazônia, Congo) e altas montanhas (Himalaia, Andes) permanecem como áreas anecúmenas devido a limitações de temperatura, umidade, relevo e acesso. [1]

O desenvolvimento econômico, especialmente a industrialização e a urbanização, reforçou a concentração populacional em áreas já favorecidas por fatores naturais. Políticas públicas, como a construção de capitais (Brasília, Abuja), incentivos à interiorização e projetos de colonização agrícola, também desempenharam papel decisivo na redistribuição populacional. [3]

> [!note] **Exemplo Global** > Cerca de 75% da população mundial vive em apenas 5% da superfície terrestre, concentrando-se em áreas ecúmenas, enquanto vastas extensões permanecem anecúmenas.

Distribuição Espacial da População no Brasil No Brasil, a distribuição populacional reflete tanto condicionantes naturais quanto processos históricos. O litoral brasileiro, especialmente o trecho entre o Nordeste e o Sul, concentra a maior parte da população devido à colonização portuguesa, à facilidade de acesso marítimo e à posterior industrialização. O Sudeste (São Paulo, Rio de Janeiro, Minas Gerais e Espírito Santo) e o Sul (Paraná, Santa Catarina e Rio Grande do Sul) apresentam as maiores densidades populacionais, impulsionadas pelo desenvolvimento industrial, infraestrutura e oferta

de empregos. [4]

A Amazônia e o Centro-Oeste representam os principais vazios demográficos do país. A ocupação da Amazônia é dificultada por fatores naturais (clima equatorial úmido, solos pobres, densa floresta) e pela ausência de infraestrutura. O Centro-Oeste, por sua vez, experimentou crescimento populacional mais recente, impulsionado pela expansão da fronteira agrícola (soja, pecuária) e pela construção de Brasília, mas ainda apresenta baixa densidade em comparação ao litoral. [5]

> [!example] **Exemplo de Vazio Demográfico: Amazônia** > A região amazônica, apesar de sua extensão, concentra menos de 10% da população brasileira, com densidades inferiores a 2 hab/km² em muitos municípios.

A urbanização acelerada, especialmente entre 1950 e 1980, foi impulsionada pelo êxodo rural e pela industrialização, resultando em metrópoles superpovoadas e periferias urbanas marcadas por desigualdades socioespaciais. O Centro-Oeste, impulsionado pela agropecuária e pela construção de Brasília, tornou-se o novo polo de atração migratória nas últimas décadas, mas ainda enfrenta desafios de infraestrutura e serviços.

> [!note] **Dado-chave** > Mais da metade da população brasileira (54,8%, ou cerca de 111 milhões de pessoas) vive a até 150 km do litoral, que representa uma fração menor do território nacional.

Padrões Globais de Concentração e Vazios Demográficos No plano global, grandes focos populacionais se concentram em regiões como o Sudeste Asiático, o Vale do Nilo, a Europa Ocidental e partes da América do Norte. Esses padrões refletem, em geral, a combinação de fatores naturais, históricos, econômicos e políticos. Por exemplo, o delta do Nilo e as planícies do Ganges-Brahmaputra são densamente povoados devido à fertilidade e à irrigação natural, enquanto áreas como o Saara, a Sibéria e a Amazônia permanecem como grandes vazios demográficos. [1]

> [!important] **Resumo Analítico** > A distribuição espacial da população é resultado de uma complexa interação entre fatores naturais (clima, relevo, recursos), históricos (colonização, rotas comerciais), econômicos (industrialização, agricultura) e políticos (políticas de ocupação, proteção ambiental). No Brasil, a concentração no litoral e os vazios demográficos do interior refletem tanto limitações ambientais quanto escolhas políticas e econômicas ao longo da história.

2.2 Grandes Movimentos Migratórios Internacionais e Intranacionais

A migração é um fenômeno central na geografia da população, envolvendo deslocamentos voluntários ou forçados, internos ou internacionais, temporários ou permanentes. Compreender suas tipologias e causas é fundamental para analisar as dinâmicas territoriais e os desafios contemporâneos.

Conceitos Fundamentais e Tipologias Migratórias > [!definition] **Migração, Emigração, Imigração, Refugiados e Deslocados Internos** > - **Migração:** Deslocamento de pessoas de um local para outro, podendo ser interna (dentro do país) ou internacional (entre países), temporária ou permanente. [6] > - **Emigração:** Saída de pessoas de seu país ou região de origem para residir em outro. > - **Imigração:** Entrada de pessoas em um país ou região diferente do seu de origem. > - **Refugiados:** Indivíduos forçados a deixar seu país devido a perseguição, guerra, violência ou graves violações de direitos humanos,

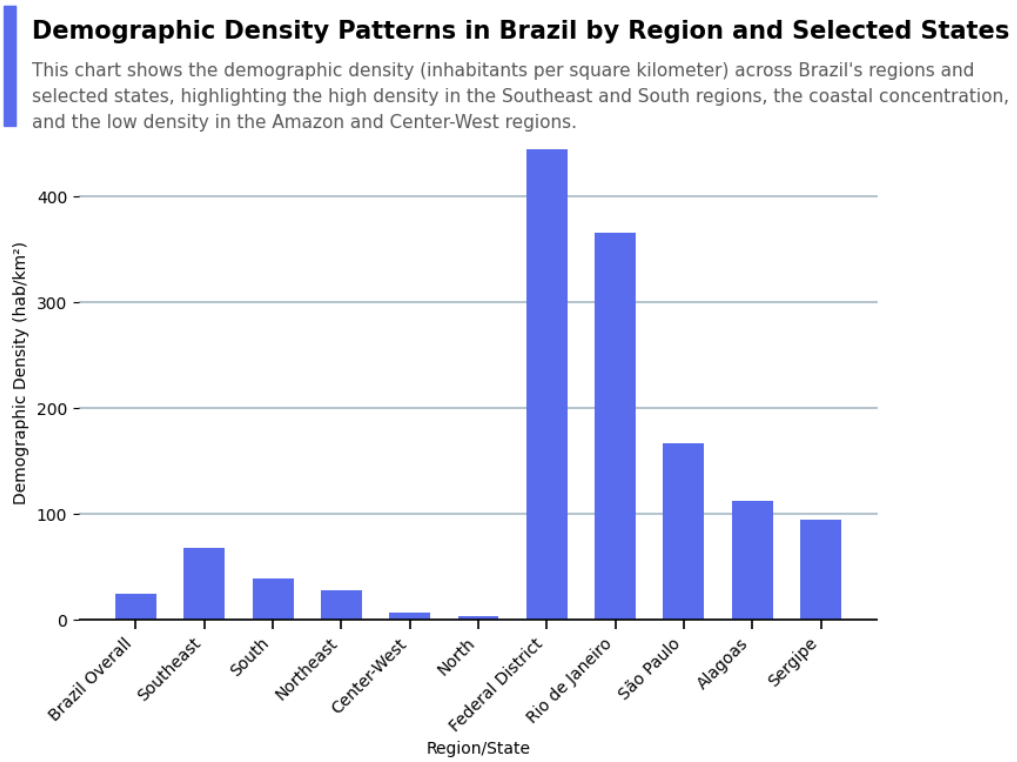

Figure 1: Demographic Density Patterns in Brazil by Region and Selected States (mundoeducacao.uol.com.br)

com direito à proteção internacional. [7] > - **Deslocados Internos:** Pessoas obrigadas a deixar suas casas, mas que permanecem dentro das fronteiras de seu próprio país, geralmente por conflitos, desastres naturais ou violência.

As tipologias migratórias incluem:

- **Espontânea (Voluntária):** Ocorre por vontade própria, geralmente motivada por fatores econômicos, sociais ou culturais, como busca por emprego, estudo ou melhores condições de vida. [8]
- **Forçada:** Decorre de fatores externos que obrigam o deslocamento, como guerras, perseguições, desastres naturais ou violações de direitos humanos. Refugiados e deslocados internos são exemplos típicos. [9]
- **Pendular:** Movimento regular e periódico entre dois locais, geralmente para trabalho ou estudo, sem mudança definitiva de residência. É comum em regiões metropolitanas, com trabalhadores que residem em cidades periféricas e se deslocam diariamente para o centro. [10]
- **Sazonal (Transumância):** Deslocamento temporário em função de estações do ano ou ciclos produtivos, como trabalhadores rurais que migram para colheitas e retornam ao local de origem após o período de trabalho. [11] [12]
- **Êxodo Rural:** Migração em massa da população rural para áreas urbanas, motivada por industrialização, mecanização agrícola e busca por melhores condições de vida. [13]

> [!note] **Migração de Retorno** > Fenômeno

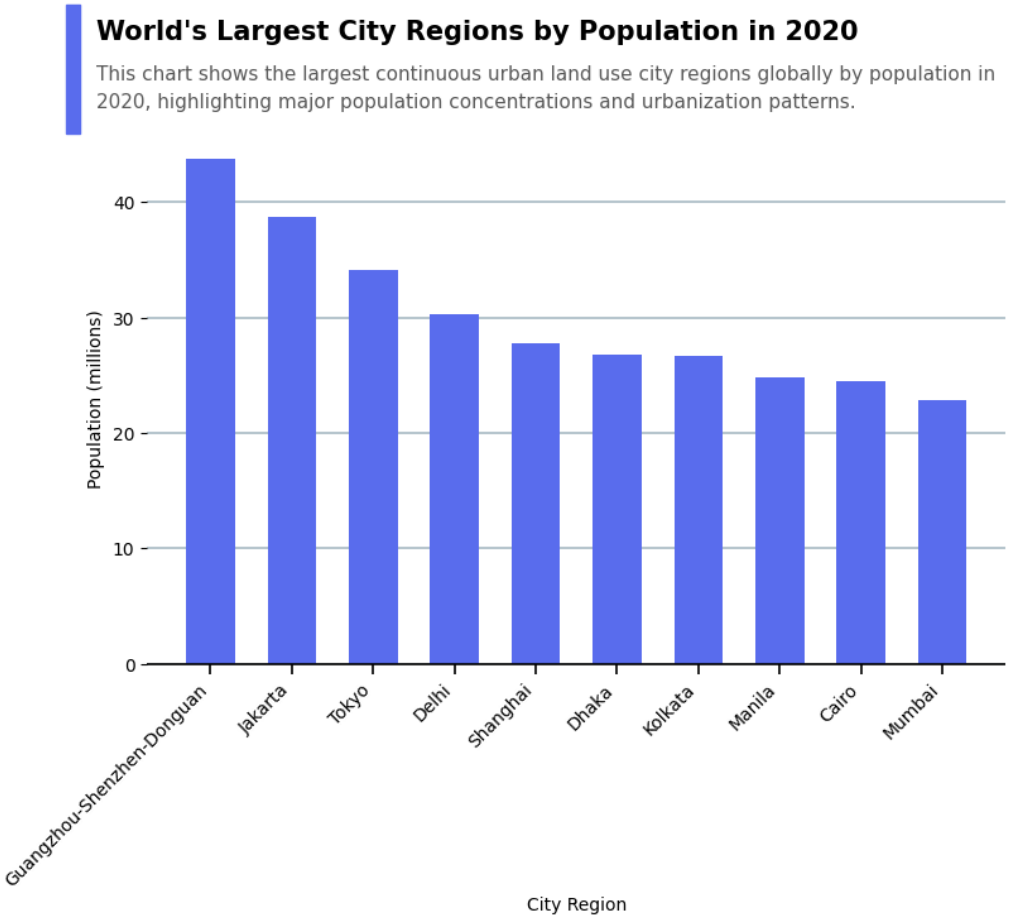

Figure 2: World's Largest City Regions by Population in 2020 (luminocity3d.org)

em que migrantes retornam à sua região ou país de origem após um período de residência em outro local, frequentemente associado a mudanças nas condições econômicas ou sociais tanto no local de origem quanto no de destino. [14]

Fluxos Migratórios Internacionais Contemporâneos: Sul-Norte e Sul-Sul Os grandes movimentos migratórios internacionais do século XXI são marcados por fluxos Sul-Norte (de países em desenvolvimento para países desenvolvidos) e Sul-Sul (entre países em desenvolvimento). As principais causas incluem:

- **Econômicas:** Busca por melhores oportunidades de trabalho e renda, fuga da pobreza e do desemprego. [15]
- **Políticas e Conflitos:** Guerras, perseguições políticas, étnicas ou religiosas, instabilidade institucional. [7]
- **Ambientais:** Desastres naturais, mudanças climáticas, degradação ambiental.

Atualmente, estima-se que mais de 280 milhões de pessoas vivam fora de seus países de origem, representando cerca de 3,6% da população mundial. [16] [17] Os principais destinos são Estados Unidos, Canadá, União Europeia, Austrália e Japão, que concentram mais de

60% dos imigrantes internacionais.

> [!example] **Crise dos Refugiados Venezuelanos** > Desde 2014, mais de 7 milhões de venezuelanos emigraram devido ao colapso econômico, hiperinflação e crise política, sendo a Colômbia, Estados Unidos, Espanha, Equador e Brasil os principais destinos. [18]

As consequências desses fluxos são múltiplas: para os países de origem, há perda de força de trabalho qualificada (fuga de cérebros), remessas financeiras e, em alguns casos, alívio de pressões demográficas. Para os países de destino, os desafios incluem integração social, pressão sobre serviços públicos, xenofobia, mas também ganhos econômicos e demográficos, especialmente em sociedades envelhecidas.

> [!important] **Remessas: Impacto Econômico** > Em 2023, as remessas para a América Latina e Caribe atingiram US$ 156 bilhões, quase o triplo de uma década atrás, sendo fundamentais para o sustento de milhões de famílias e para a estabilidade econômica de países como El Salvador, Honduras e Haiti.

Migrações Internas no Brasil O Brasil apresenta uma rica história de movimentos migratórios internos, que moldaram sua urbanização, estrutura produtiva e distribuição populacional.

- **Êxodo Rural:** Entre 1950 e 1980, milhões de brasileiros migraram do campo para as cidades, impulsionando a urbanização e a formação de metrópoles. Esse processo foi motivado pela mecanização agrícola, concentração fundiária e industrialização urbana.
- **Migrações Inter-Regionais:** O fluxo Nordeste-Sudeste foi o mais expressivo, com nordestinos buscando melhores condições de vida nas cidades industriais do Sudeste (São Paulo, Rio de Janeiro). Posteriormente, fluxos de sulistas para o Centro-Oeste e Norte acompanharam a expansão da fronteira agrícola. [19]
- **Migração de Retorno:** A partir dos anos 1980, com a estagnação econômica do Sudeste e o crescimento de polos regionais no Nordeste e Centro-Oeste, observou-se o retorno de migrantes às suas regiões de origem. [20]
- **Migração Pendular:** O crescimento das regiões metropolitanas intensificou os movimentos pendulares, com trabalhadores residindo em cidades periféricas e se deslocando diariamente para os centros urbanos.

> [!example] **Construção de Brasília** > A transferência da capital para o interior, em 1960, atraiu milhares de migrantes de todo o país, especialmente do Nordeste, para a construção de Brasília e a ocupação do Centro-Oeste. [21]

> [!note] **Migração de Retorno** > Nas últimas décadas, políticas de desenvolvimento regional e programas sociais estimularam o retorno de migrantes ao Nordeste, invertendo parcialmente o fluxo histórico de saída.

Migração, Refúgio e Deslocamento Forçado O Brasil também se destaca como país receptor de migrantes internacionais e refugiados, especialmente nas últimas décadas. Entre 2010 e 2024, o país recebeu cerca de 2,3 milhões de migrantes, incluindo 146 mil refugiados reconhecidos, principalmente da Venezuela, Síria e República Democrática do Congo.

A legislação brasileira, notadamente a Lei nº 9.474/1997 (Estatuto dos Refugiados) e a Lei nº 13.445/2017 (Lei de Migração), garante direitos e proteção a migrantes e refugiados, alinhando-se aos princípios internacionais de

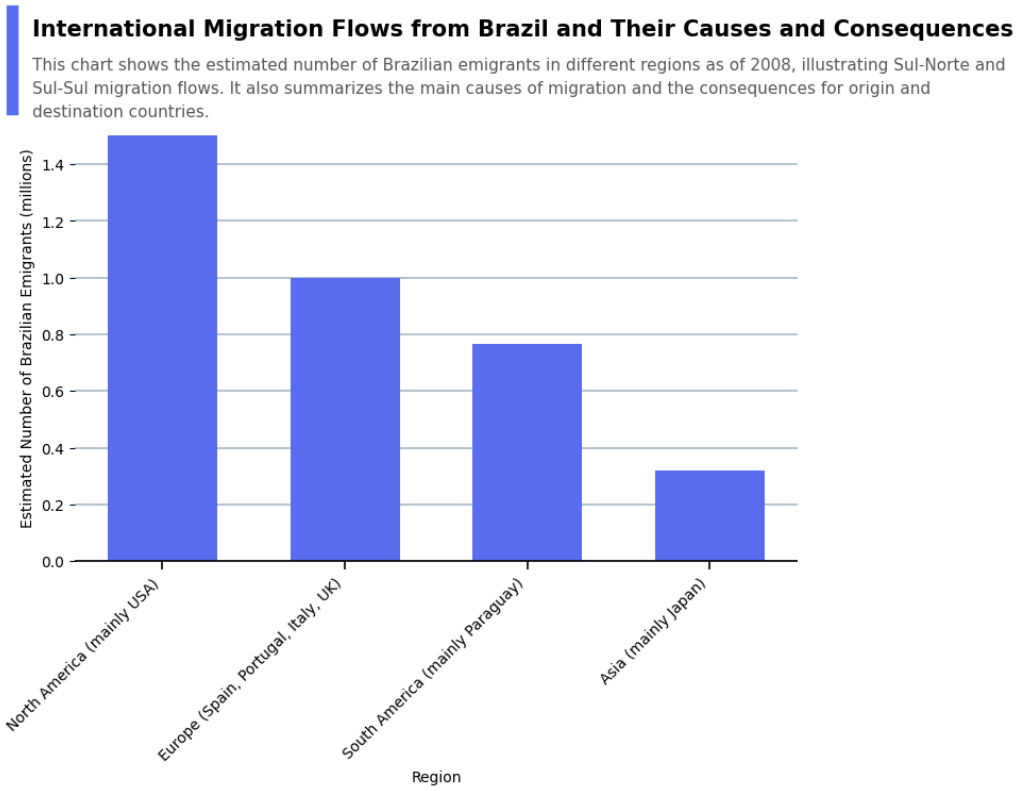

Figure 3: International Migration Flows from Brazil and Their Causes and Consequences (scielo.br)

não discriminação e não devolução (non-refoulement). [22]

> [!important] **Distinção Legal: Refugiado x Imigrante** > Todo refugiado é um migrante, mas nem todo migrante é refugiado. O refugiado é forçado a se deslocar por risco à vida, enquanto o imigrante se desloca voluntariamente, podendo retornar ao país de origem. [23]

Migração e Mudanças Climáticas O impacto das mudanças climáticas sobre os fluxos migratórios internos e internacionais tem se intensificado. Secas prolongadas, enchentes, desertificação e eventos extremos têm provocado deslocamentos forçados, especialmente em regiões vulneráveis como o semiárido nordestino e a Amazônia.

> [!important] **Projeções e Estudos Recentes** > O Banco Mundial estima que até 2050, 17 milhões de pessoas na América Latina poderão ser deslocadas internamente por motivos climáticos, sendo o Brasil um dos países mais afetados.

2.3 Dinâmica Populacional e Indicadores da Qualidade de Vida das Populações

A dinâmica populacional refere-se às transformações quantitativas e qualitativas da população ao longo do tempo, influenciando e sendo influenciada pelos movimentos migratórios e pela distribuição espacial.

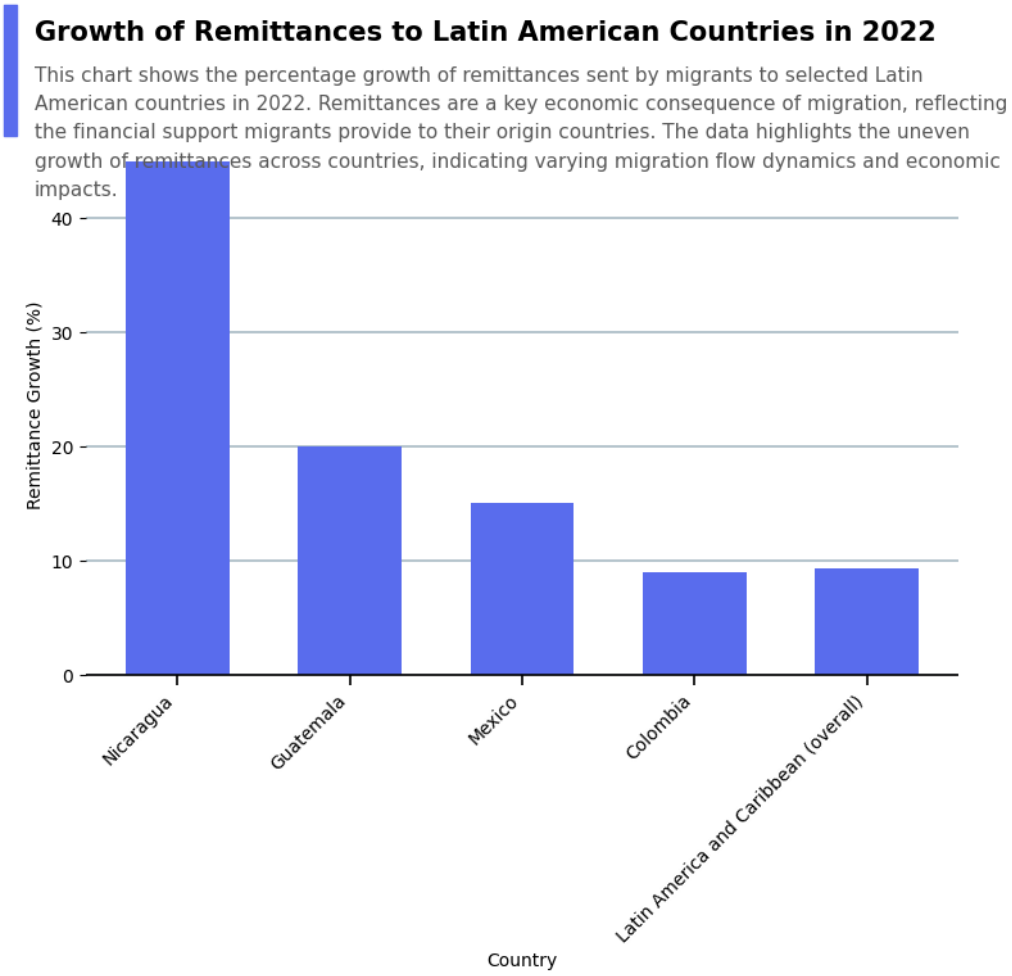

Figure 4: Growth of Remittances to Latin American Countries in 2022 (noticias.uol.com.br)

Principais Conceitos e Indicadores Demográficos

- **Taxa de Natalidade:** Número de nascimentos por mil habitantes em determinado período.
- **Taxa de Mortalidade:** Número de óbitos por mil habitantes.
- **Taxa de Fecundidade:** Número médio de filhos por mulher em idade fértil.
- **Crescimento Vegetativo (Natural):** Diferença entre natalidade e mortalidade.
- **Transição Demográfica:** Modelo que descreve a passagem de altas taxas de natalidade e mortalidade para níveis baixos, geralmente associada ao desenvolvimento socioeconômico. [24]

> [!definition] **Transição Demográfica** > Processo pelo qual uma sociedade passa de um regime demográfico tradicional (altas taxas de natalidade e mortalidade) para um regime moderno (baixas taxas), com implicações profundas para a estrutura etária e as políticas públicas.

A estrutura etária da população é representada por pirâmides populacionais, que revelam o perfil demográfico de uma sociedade:

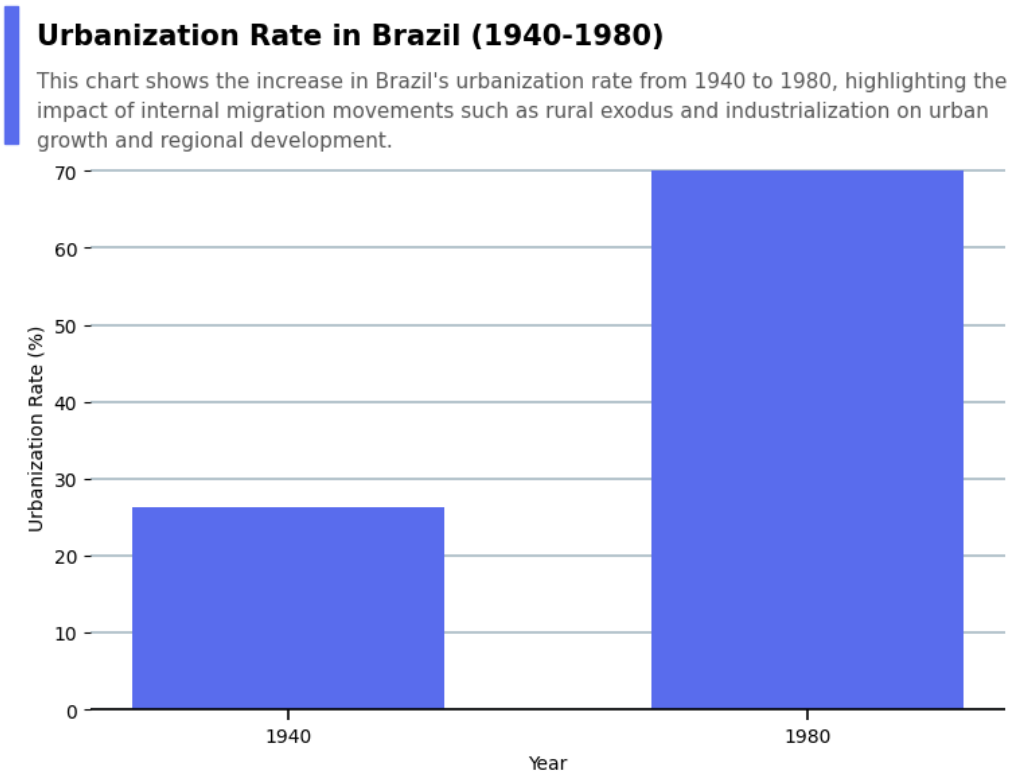

Figure 5: Urbanization Rate in Brazil (1940-1980) (plataforma.hexag.online)

- **Pirâmide Jovem:** Base larga, predominância de crianças e jovens, típica de países em desenvolvimento.
- **Pirâmide Adulta:** Base e topo mais equilibrados, indicando transição demográfica.
- **Pirâmide Envelhecida:** Topo largo, predominância de idosos, comum em países desenvolvidos e em transição avançada.

No Brasil, observa-se um rápido envelhecimento populacional, com redução da taxa de fecundidade (abaixo de 1,8 filhos por mulher) e aumento da expectativa de vida (cerca de 76 anos em 2023). Isso implica desafios para a previdência, saúde pública e mercado de trabalho, mas também oportunidades de bônus demográfico, com maior proporção de população economicamente ativa. [24]

> [!note] **Bônus Demográfico** > Período em que a proporção de pessoas em idade ativa (15-64 anos) é maior que a de dependentes (crianças e idosos), favorecendo o crescimento econômico. No Brasil, esse bônus está se esgotando, e o envelhecimento populacional impõe novos desafios.

Indicadores de Qualidade de Vida A avaliação da qualidade de vida e das desigualdades socioespaciais utiliza indicadores compostos e específicos:

- **Índice de Desenvolvimento Humano (IDH):** Mede desenvolvimento a partir de renda per capita, expectativa de vida e escolaridade. O Brasil apresenta IDH médio (0,786 em 2023), com grandes disparidades regionais. [[IDH PNUD]]
- **Coeficiente de Gini:** Avalia a desigualdade de renda (0 = igualdade perfeita; 1 = de-

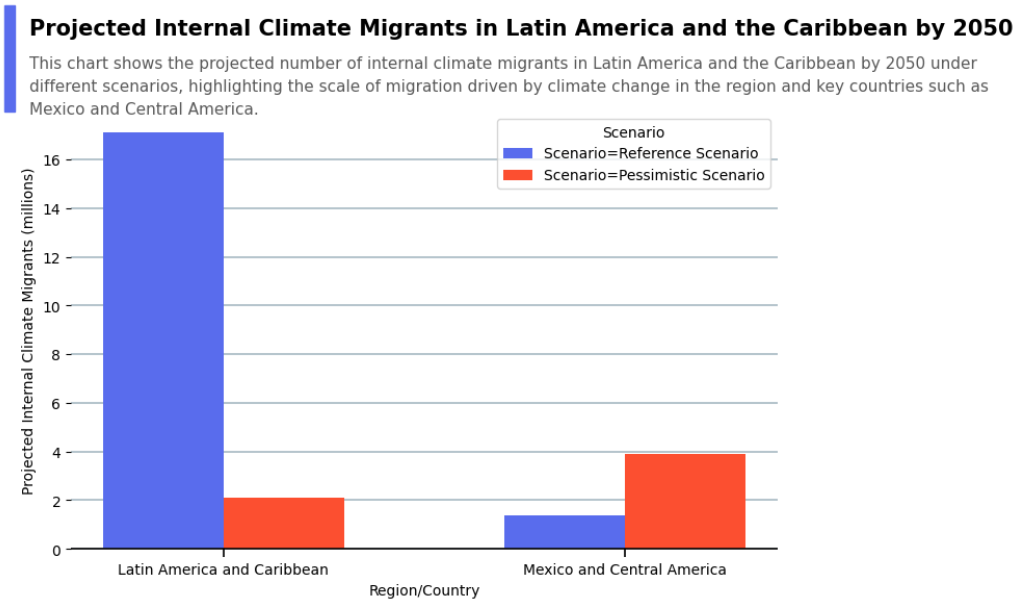

Figure 6: Projected Internal Climate Migrants in Latin America and the Caribbean by 2050 (frontiersin.org)

sigualdade máxima). O Brasil tem um dos maiores coeficientes do mundo (em torno de 0,53), refletindo forte concentração de renda. [[IDH PNUD]]

- **Expectativa de Vida ao Nascer:** Indica as condições de saúde e bem-estar; no Brasil, varia de 70 anos (regiões mais pobres) a 80 anos (regiões mais ricas).
- **Taxa de Mortalidade Infantil:** Número de óbitos de crianças menores de 1 ano por mil nascidos vivos; indicador sensível às condições de saúde, saneamento e acesso a serviços. [[IDH PNUD]]
- **Taxa de Analfabetismo:** Percentual da população acima de 15 anos que não sabe ler e escrever; no Brasil, ainda supera 6%, com concentração nas regiões Norte e Nordeste. [[IDH PNUD]]

> [!important] **Desigualdades Regionais no Brasil** > O Sudeste e o Sul concentram os melhores indicadores de qualidade de vida, enquanto o Norte e o Nordeste apresentam maiores desafios em saúde, educação e renda. [[IDH PNUD]]

A análise desses indicadores revela que a distribuição, os movimentos e a estrutura da população estão profundamente interligados às condições de vida e ao desenvolvimento dos territórios. Migrações internas e internacionais, por exemplo, são tanto causa quanto consequência das desigualdades regionais e da busca por melhores oportunidades.

> [!note] **Desigualdades Demográficas e Espaciais** > Os indicadores de qualidade de vida revelam profundas desigualdades regionais, raciais e de gênero no Brasil e na América Latina, com o Norte e Nordeste, populações negras, indígenas e mulheres sistematicamente em desvantagem.

Conclusão

A Geografia da População revela-se como um campo dinâmico e multifacetado, no qual

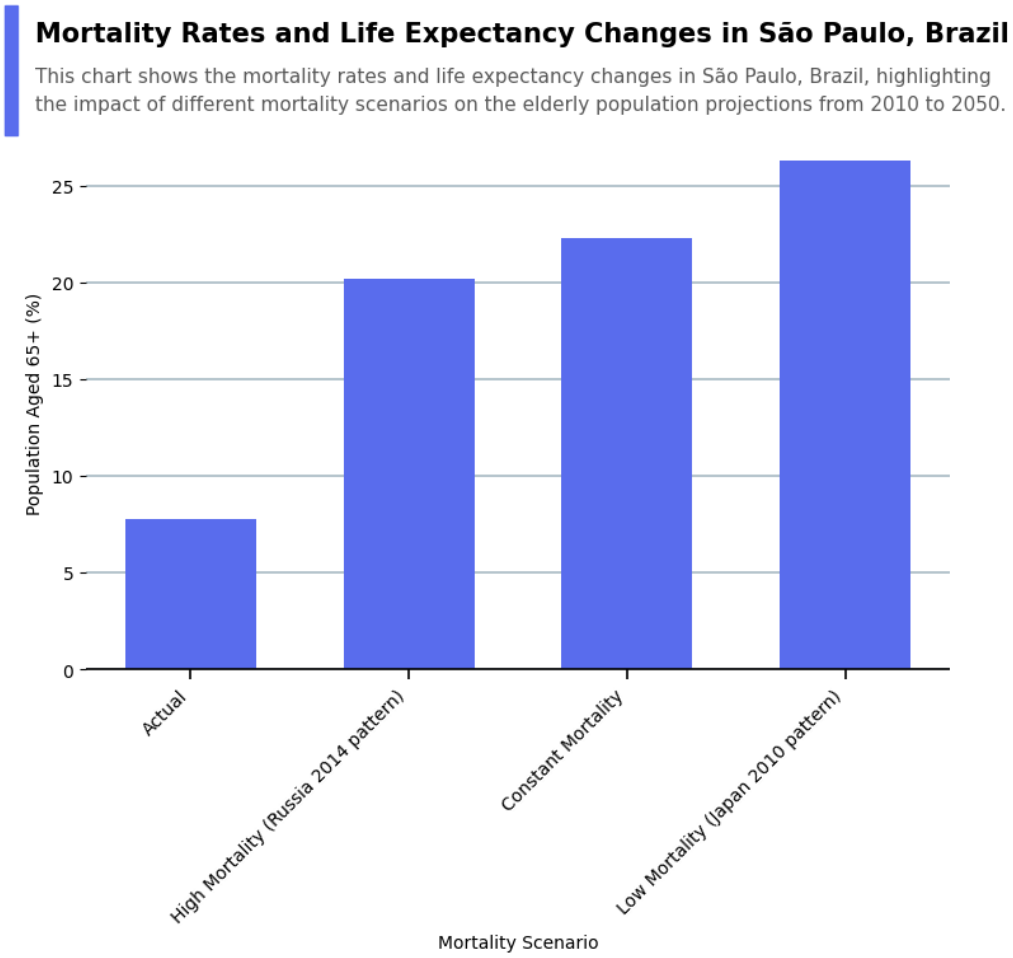

Figure 7: Mortality Rates and Life Expectancy Changes in São Paulo, Brazil (scielo.br)

a distribuição espacial, os movimentos migratórios e a dinâmica demográfica se entrelaçam para moldar as sociedades contemporâneas. No Brasil, os desafios de concentração populacional, migrações internas e internacionais, envelhecimento demográfico e desigualdades regionais exigem análise crítica e políticas inovadoras. A urbanização acelerada, a migração de retorno, o envelhecimento populacional e a crescente presença de migrantes internacionais impõem a necessidade de políticas integradas e sensíveis às múltiplas dimensões da questão populacional. No cenário internacional, a intensificação dos fluxos Sul-Norte e Sul-Sul, as crises de refugiados e o papel das remessas evidenciam a centralidade da migração nas dinâmicas globais, exigindo cooperação internacional e respostas inovadoras para promover o desenvolvimento humano e a inclusão. Para o diplomata, compreender esses fenômenos é fundamental para atuar na promoção do desenvolvimento, da justiça social e da integração internacional.

Questões para Autoavaliação (Active Recall)

> [!question] 1. Explique a diferença entre mi-

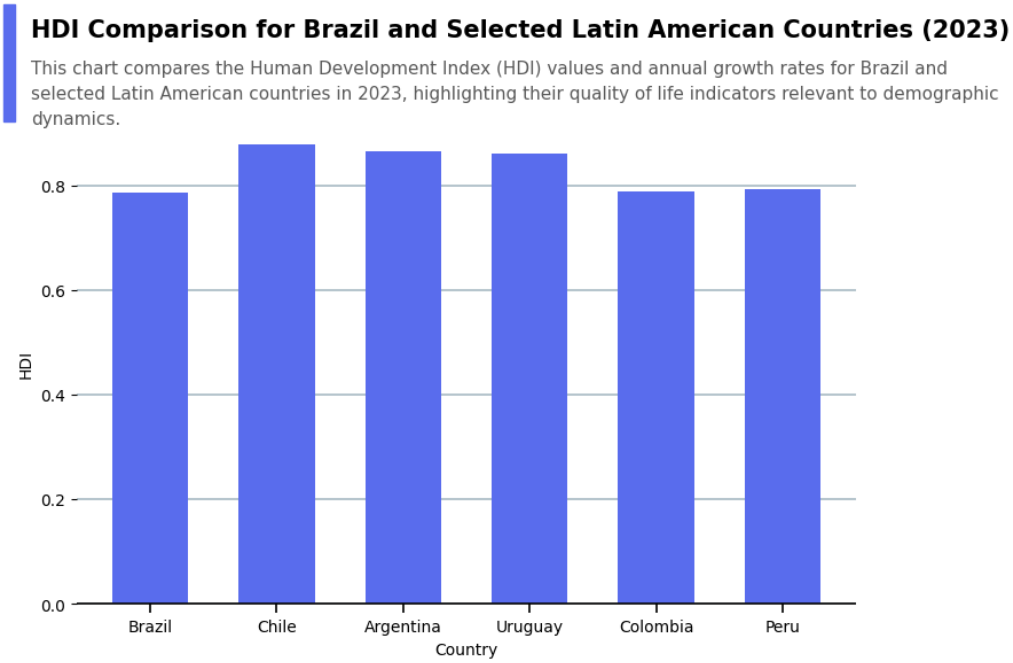

Figure 8: HDI Comparison for Brazil and Selected Latin American Countries (2023) (pt.wikipedia.org)

gração espontânea e migração forçada, ilustrando com exemplos brasileiros e internacionais. > [!question] 2. Analise como o êxodo rural e as migrações inter-regionais moldaram a urbanização e a distribuição populacional no Brasil ao longo do século XX. > [!question] 3. Discuta as implicações do envelhecimento populacional para a estrutura etária e os desafios socioeconômicos do Brasil, relacionando com os conceitos de transição demográfica e bônus demográfico.

> [!note] **Recomenda-se complementar este material com leituras acadêmicas e dados atualizados do IBGE, ACNUR, PNUD e outras fontes oficiais para aprofundamento e atualização dos indicadores e exemplos.**

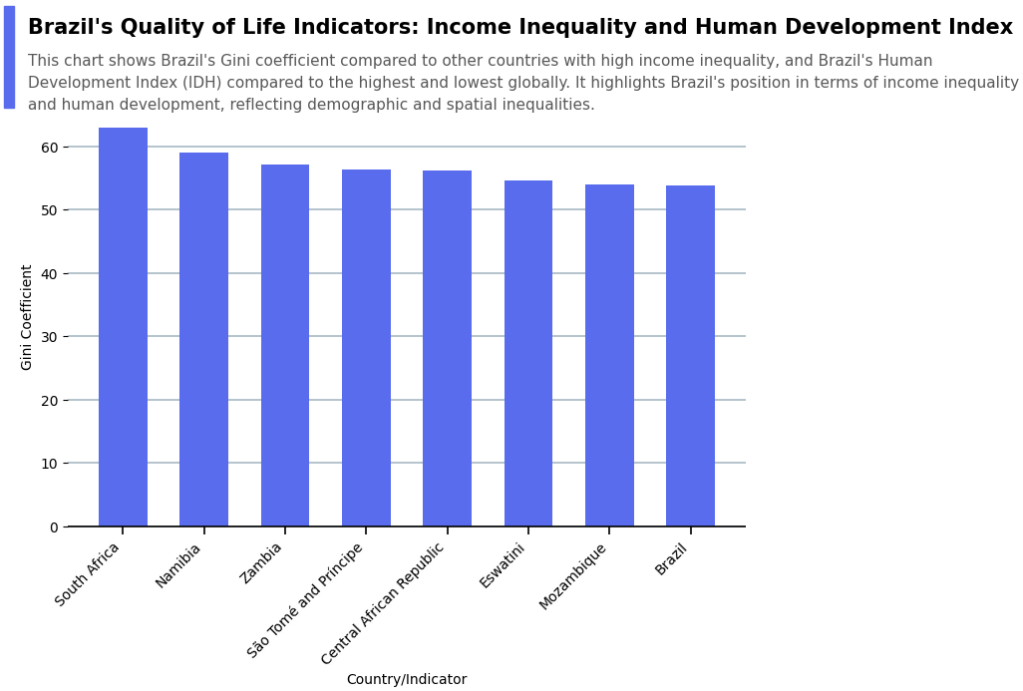

Figure 9: Brazil's Quality of Life Indicators: Income Inequality and Human Development Index (noticias.uol.com.br)

References

1. **América Latina registra a maior queda na fecundidade do mundo: 'O mundo está muito difícil para trazer mais gente'**. Emanuelle Bordallo; Emanuelle Bordallo; Emanuelle Bordallo. https://oglobo.globo.com
2. **Case study - Rio de Janeiro, Brazil - Challenges and opportunities for urban areas - OCR - GCSE Geography Revision - OCR - BBC Bitesize**. BBC Bitesize. January 10, 2017. https://www.bbc.co.uk
3. **Concentração espacial da produção e desigualdades sociais**. Pochmann et al. February 21, 2020. https://www.scielo.br
4. **Crescimento populacional: no mundo e no Brasil - Mundo Educação**. Mateus Campos. August 07, 2008. https://mundoeducacao.uol.com.br
5. **Expectativa de vida no Brasil em 2023 chega a 76,4 anos, diz IBGE | Agência Brasil**. https://agenciabrasil.ebc.com.br
6. **Fluxos migratórios: tipos, causas, consequências e desafios**. https://aprovatotal.com.br
7. **Migração Internacional - Mundo Educação**. Wagner de Cerqueira e Francisco. May 06, 2010. https://mundoeducacao.uol.com.br
8. **Migração de retorno ou regresso - o que é, exemplos - Geografia**. Felipe Araújo. https://www.infoescola.com
9. **Migração: conceito, tipos, exemplos, causas - Brasil Escola**. Paloma Guitarrara. March 13, 2012. https://brasilescola.uol.com.br
10. **Migração: entenda o que é e os principais tipos**. Vinícius Marques. July 16, 2020. https://www.todamateria.com.br
11. **Migrações no Brasil - Mundo Educação**. Wagner de Cerqueira e Francisco. December 11, 2007. https://mundoeducacao.uol.com.br
12. **Migrações — Enciclopédia Latinoamericana**. https://latinoamericana.wiki.br
13. **O que é o IDH | United Nations Development Programme**. https://www.undp.org
14. **O que é refúgio**. Ministério da Justiça e Segurança Pública. https://www.gov.br
15. **Pirâmide etária: o que é, para que serve, tipos - Mundo Educação**. Mateus Campos. July 22, 2013. https://mundoeducacao.uol.com.br
16. **População - Migrações no Brasil**. Proenem. December 17, 2018. https://proenem.com.br
17. **População - transição demográfica**. Proenem. October 29, 2018. https://proenem.com.br
18. **Principais Migrações Inter-regionais no Brasil - Brasil Escola**. Júlio César Lázaro da Silva. May 28, 2013. https://brasilescola.uol.com.br
19. **Quando usar o termo migrante, refugiado ou pessoa deslocada? | As Nações Unidas no Brasil**. https://brasil.un.org
20. **Refugiado e Imigrante, entenda quais as diferenças entre os termos - Fundo Brasil**. Base Digital. November 12, 2024. https://www.fundobrasil.org.br
21. **Refugiados: 3 gráficos que mostram o aumento histórico no mundo - BBC News Brasil**. BBC News Brasil. June 25, 2024. https://www.bbc.com
22. **Relatório CEPAL 2024: Redução da pobreza na América Latina atinge níveis históricos, mas desigualdade e desproteção social ainda preocupam | IFZ**. https://ifz.org.br
23. **Resumo de Distribuição da População Mundial: Fatores e Implicações**. Teachy. https://www.teachy.com.br

24. **Taxa de natalidade e taxa de mortalidade - Brasil Escola**. Rafaela Sousa. August 05, 2014. https://brasilescola.uol.com.br
25. **Taxa de natalidade e taxa de mortalidade - Mundo Educação**. Rafaela Sousa. September 12, 2018. https://mundoeducacao.uol.com.br
26. **Tipos de Migrações em Geografia | Descomplica**. Descomplica. https://descomplica.com.br
27. **Transição demográfica: o que é, causas, fases - Brasil Escola**. Paloma Guitarrara. April 30, 2015. https://brasilescola.uol.com.br
28. **Urbanização brasileira: causas e consequências - Brasil Escola**. Paloma Guitarrara. May 30, 2007. https://brasilescola.uol.com.br
29. **Áreas ecúmenas e anecúmenas. | PPT**. August 12, 2013. https://www.slideshare.net
30. **Índice de Gini: o que significa, como é medido - Brasil Escola**. Paloma Guitarrara. June 12, 2015. https://brasilescola.uol.com.br

0358f307-6eeb-42fb-9d85-7b1265db0100